Руководство пользователя.

На основной странице проекта по адресу https://tarihgis.ru/ (Рис.1) необходимо выбрать способ отображения данных о сословном составе населения в трёх различных способах упорядочивания сведений путём нажатия на соответствующую кнопку синего цвета, либо нажав на пункт меню с соответствующем названием наверху страницы:

- Населённые пункты

- Сословия

- Ревизии

Рис.1. Первоначальная страница проекта.

После выбора желаемого раздела нужно настроить параметры отбора имеющихся сведений (Рис.2), что позволяет максимально точно настроить формируемую таблицу.

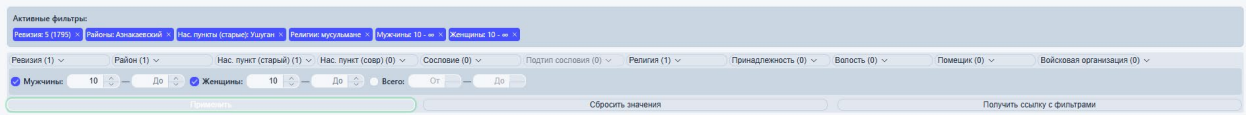

Рис.2.Конструктор пользовательских запросов.

Для создания пользовательского запроса используются справочники с возможностью и численные значения, сформированные на основе всего массива загружаемых данных.

Номер ревизии с указанием года и возможностью выбора нескольких значений (Рис.3)

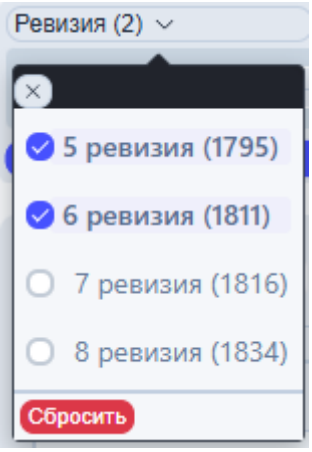

Рис.3. Пример выбора двух ревизий.

Верхняя надпись «Ревизия (2)» говорит нам о том, что выбраны два значения из справочника «Ревизии».

Для детализации сведений о географическом положении предназначен блок фильтров «Район», содержащий название в современном административном делении, «Нас. пункт (старый)» - название в ревизских записях и «Нас. пункт (совр.)» - современное название (Рис.4)

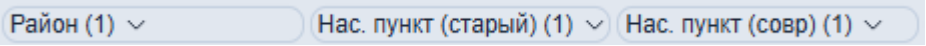

Рис.4. Блок выбора административной единицы.

Выбор одного или нескольких районов осуществляется через справочник районов (Рис.5).

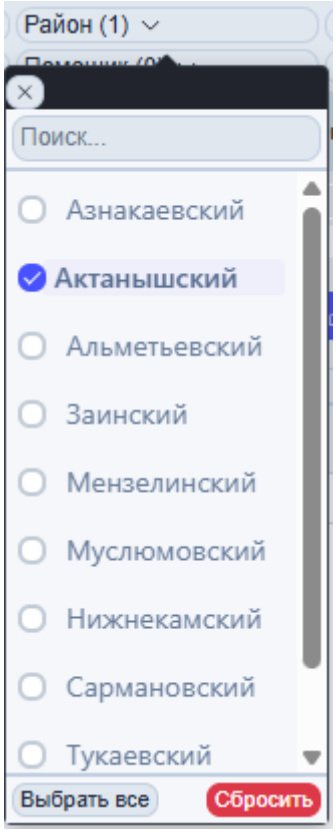

Рис.5. Значения из справочника районов.

При необходимости можно выбрать населённый пункт согласно его наименованию в ревизских записях (Рис.6), при этом предлагаемый перечень населённых пунктов отображается в соответствии с выбранным районом.

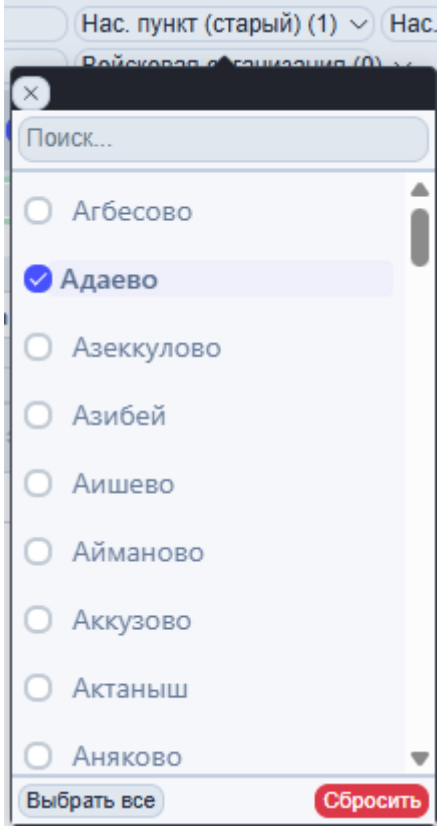

Рис.6. Выбор населённых пунктов согласно историческим названиям.

Основным справочником для построения запросов является справочник «Сословие», содержащий перечень всех сословий из хранимых в этой системе ревизских записей (Рис.7).

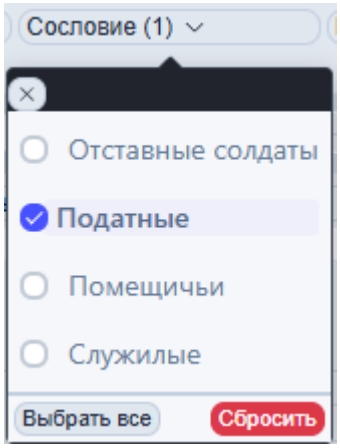

Рис.7. Подбор одного или нескольких наименований сословий для построения выборки.

Остальные значения из справочников «Подтип сословия», «Религия», «Принадлежность», «Волость», «Помещик» и «Войсковая организация» при необходимости их использования формируются по такому же принципу.

Для отбора данных по численному признаку используется набор диапазонов количества мужчин и женщин (Рис.8).

Рис.8. Пример установки количественных значений упоминаемого в ревизиях населения.

При выборе значений из справочников и установке количественных диапазонов числовых значений формируется область показа будущего запроса к базе данных (Рис.9)

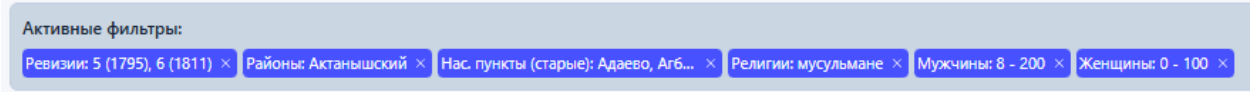

Рис.9. Пример предварительного показа выбранных значений для формируемой выборки.

После выбора желаемых значений фильтров необходимо нажать мерцающую кнопку «Применить» для того, чтобы произошёл отбор данных (Рис.10).

Рис.10. Основная кнопка для применения всех значений выборки для автоматического формирования запроса к базе данных и выдачи результата.

В разделе «Населённые пункты» появляется режим отображения данных в зависимости от предпочтений пользователя просмотра результатов выборки, а именно, «Список» - предоставление данных в виде таблицы, «Карта» - нанесение данных на картографическую основу, «Разделить» - совмещение табличного и картографического представления и «Geojson» - представление выборки данных в виде файла в международном формате обмена данными (Рис.11).

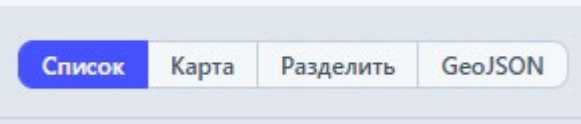

Рис.11. Переключение режимов отображения выбранных наборов данных.
Выбор режима «Список» позволяет просматривать выбранные данные в виде таблицы (Рис.12)

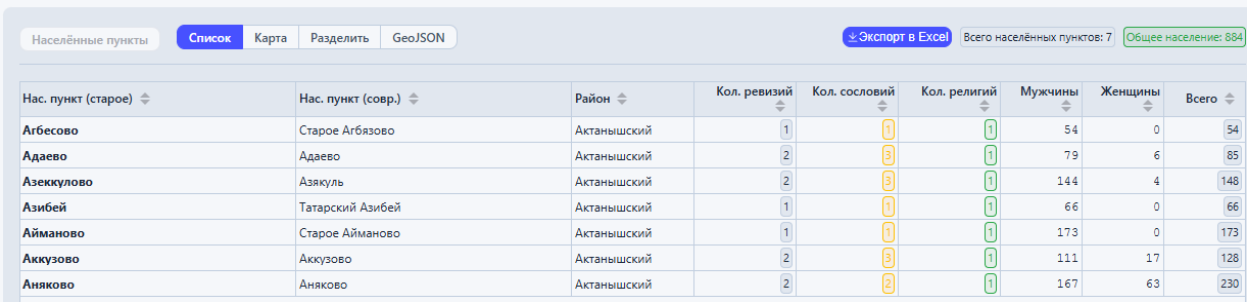

Нас. пункт (старое)	Нас. пункт (совр.)	Район	Кол. ревизий	Кол. сословий	Кол. религий	Мужчины	Женщины	Всего
Агбесово	Старое Агбязово	Актанышский	1	1	1	54	0	54
Адаево	Адаево	Актанышский	2	3	1	79	6	85
Азеккулово	Азякуль	Актанышский	2	3	1	144	4	148
Азибей	Татарский Азибей	Актанышский	1	1	1	66	0	66
Айманово	Старое Айманово	Актанышский	1	1	1	173	0	173
Аккузово	Аккузово	Актанышский	2	3	1	111	17	128
Аняково	Аняково	Актанышский	2	2	1	167	63	230

Рис.12. Таблица Населённых пунктов, созданная на основе выборки.

Существует возможность экспорта таблицы в стандартный формат Excel по нажатию на кнопку «Экспорт в Excel» (Рис.13).

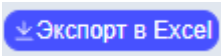

Рис.13. Кнопка экспорта таблицы в формат Excel.

При выборе режима «Карта» появляется возможность просмотра результатов выборки на современной карте OpenStreetMap ((Рис.14).

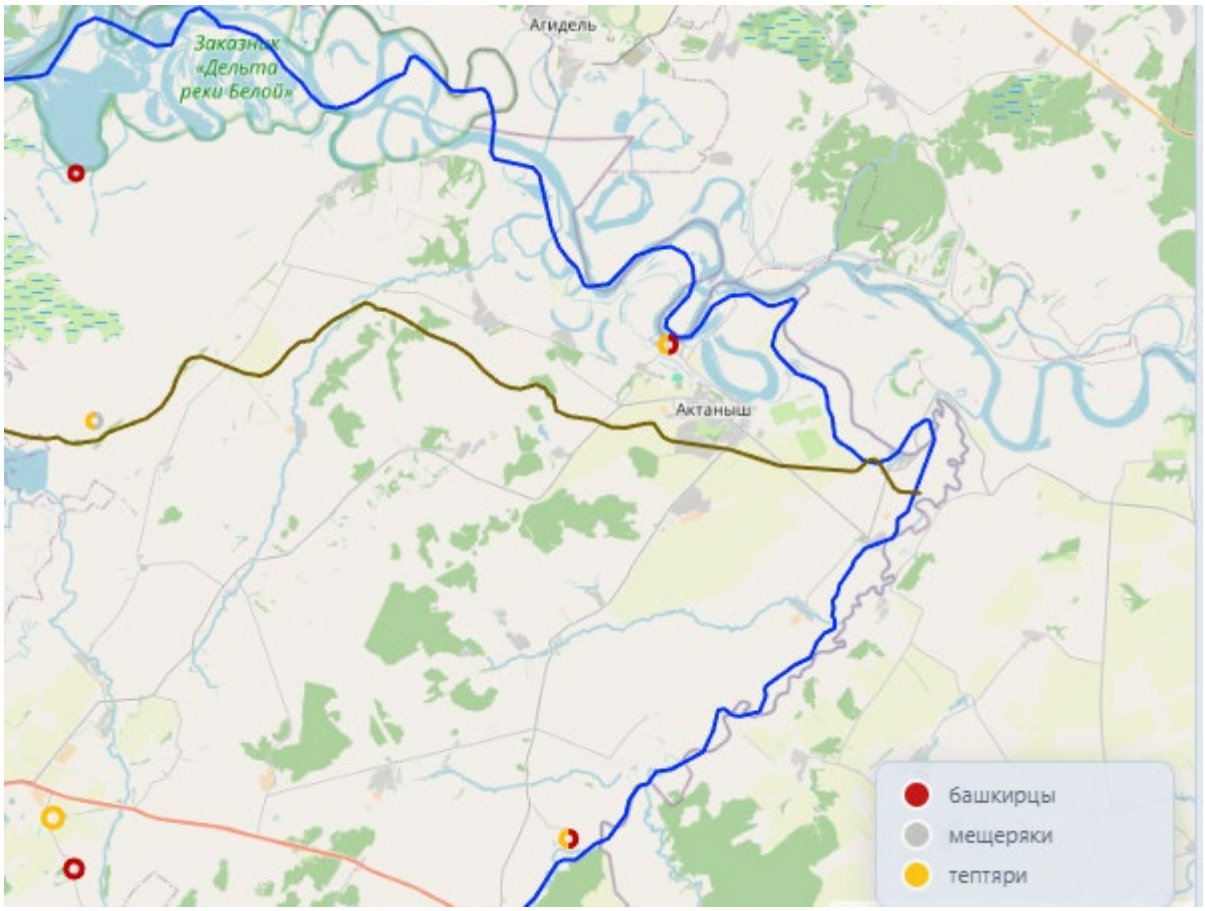

Рис.14. Картографическое отображение выборки данных.

При выборе варианта просмотра «Разделить» появляется возможность одновременного просмотра и таблицы, и карты (Рис.15).

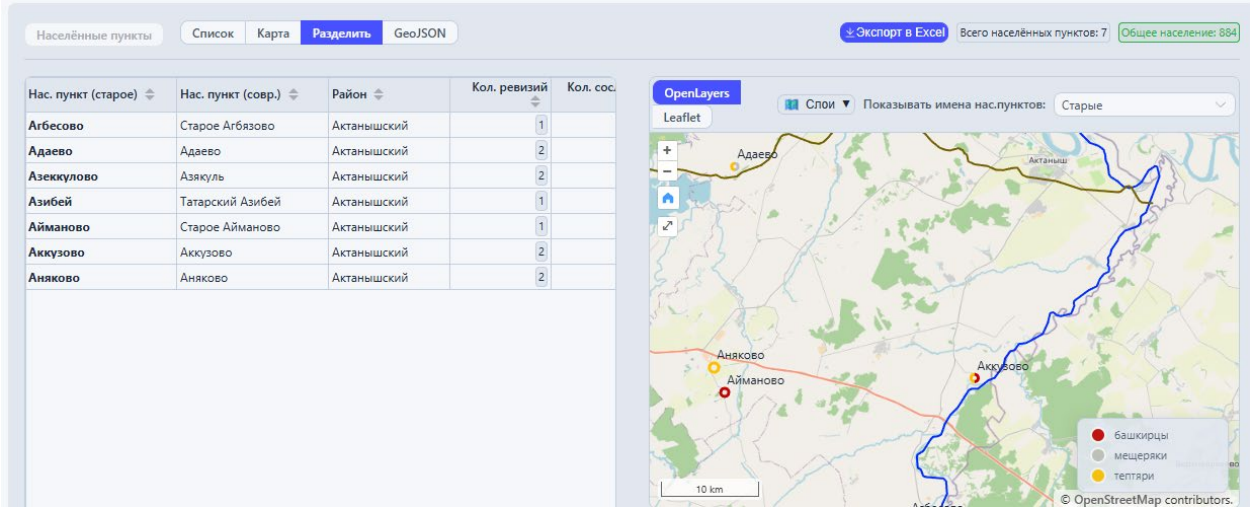

Рис.15. Режим совместного просмотра табличных и пространственных данных.

После выбора «GeoJSON» есть возможность экспортировать результаты выборки в общепринятый в международном сообществе формат (Рис.16).

Экспорт Копировать


```
{
  "type": "FeatureCollection",
  "features": [
    {
      "type": "Feature",
      "geometry": {
        "type": "Point",
        "coordinates": [
          53.832091,
          55.393416
        ]
      },
      "properties": {
        "id": 4630,
        "name_old": "Агбесово",
        "name_modern": "Старое Агбязово",
        "district_name": "Актанышский",
        "population": {
          "male": 54,
          "female": 0,
          "total": 54
        },
```


Рис.16. Фрагмент пригодного для экспорта файла в формате GeoJSON.

Двойное нажатие на строку таблицы вызывает появление детальных сведений (Рис.17).

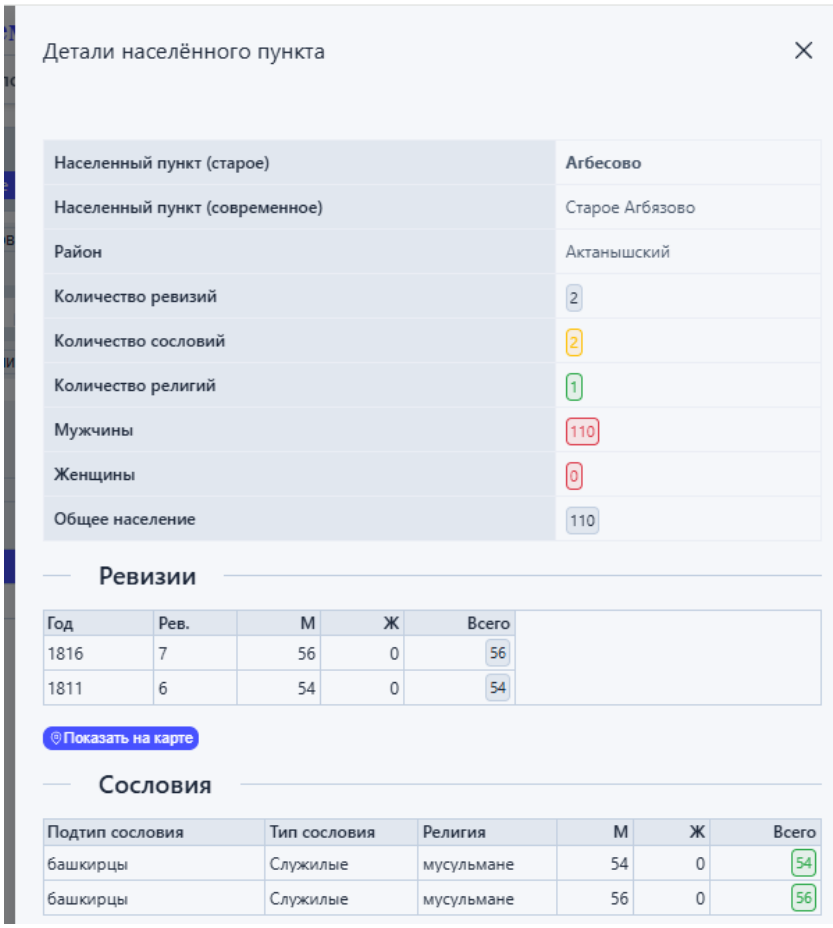

Детали населённого пункта

Населенный пункт (старое)	Агбесово
Населенный пункт (современное)	Старое Агбязово
Район	Актанышский
Количество ревизий	2
Количество сословий	2
Количество религий	1
Мужчины	110
Женщины	0
Общее население	110

Ревизии

Год	Рев.	М	Ж	Всего
1816	7	56	0	56
1811	6	54	0	54

Показать на карте

Сословия

Подтип сословия	Тип сословия	Религия	М	Ж	Всего
башкирцы	Служилые	мусульмане	54	0	54
башкирцы	Служилые	мусульмане	56	0	56

Рис. 17. Детальные сведения о населённом пункте.

В разделе «Сословия» используются те же самые значения выборки, но итоговая таблица строится на основе типов сословий (Рис.18).

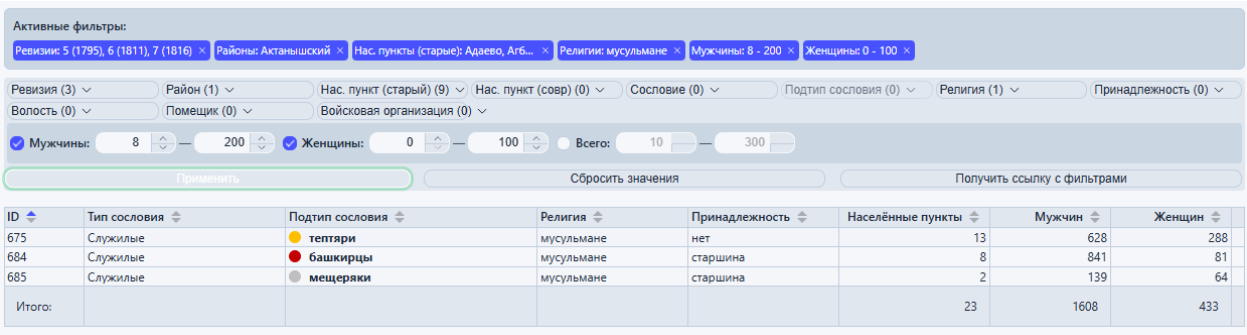

Активные фильтры:
Ревизии: 5 (1795), 6 (1811), 7 (1816) × | Районы: Актанышский × | Нас. пункты (старые): Адаево, Агб... × | Религии: мусульмане × | Мужчины: 8 - 200 × | Женщины: 0 - 100 ×

Ревизия (3) | Район (1) | Нас. пункт (старый) (9) | Нас. пункт (совр) (0) | Сословие (0) | Подтип сословия (0) | Религия (1) | Принадлежность (0) | Волость (0) | Помещик (0) | Войсковая организация (0)

Мужчины: 8 — 200 | Женщины: 0 — 100 | Всего: 10 — 300

Применить | Сбросить значения | Получить ссылку с фильтрами

ID	Тип сословия	Подтип сословия	Религия	Принадлежность	Населённые пункты	Мужчин	Женщин
675	Служилые	тептяри	мусульмане	нет	13	628	288
684	Служилые	башкирцы	мусульмане	старшина	8	841	81
685	Служилые	мещеряки	мусульмане	старшина	2	139	64
Итого:					23	1608	433

Рис.18. Таблица сословий с количественном выражением состава населения.

Раздел «Ревизии» построен в виде таблицы ревизских записей, где каждая строка таблицы соответствует строке ревизской записи, но при этом разделена на столбцы согласно типам данных (Рис.19).

Активные фильтры:

Ревизия: 5 (1795) × Религии: мусульмане ×

Ревизия (1) | Район (0) | Нас. пункт (старый) (0) | Нас. пункт (совр) (0) | Сословие (0) | Подтип сословия (0) | Религия (1) | Принадлежность (0) | Волость (0) | Помещик (0) | Войсковая организация (0)

Мужчины: От — До | Женщины: От — До | Всего: 10 — 300

Применить | Сбросить значения | Получить ссылку с фильтрами

Столбцы | Экспорт в Excel | Всего записей: 285

Рев.	Нас. пункт (старый)	Нас. пункт (совр.)	Район	Подтип сословия	Сословие	Религия	Принадлежность	М	Ж	Всего	Волость	Пс
5	Абдулово по речке Сухие Бишанды	Старое Абдулово	Тукаевский	тептяри	Служилые	мусульмане	нет	127	123	250		
5	Абдулово по речке Сухие Бишанды	Старое Абдулово	Тукаевский	ясачные татары	Податные	мусульмане	волость	1	2	3		
5	Адаево	Адаево	Актанышский	тептяри	Служилые	мусульмане	нет	8	6	14		
5	Адрекли на речке Адрекли	Атрякле	Мензелинский	тептяри	Служилые	мусульмане	нет	73	63	136		
5	Азалаково	Азалаково	Сармановский	тептяри	Служилые	мусульмане	нет	79	82	161		
5	Азеккулово	Азякуль	Актанышский	тептяри	Служилые	мусульмане	нет	3	4	7		
5	Аишево	Аишево	Актанышский	тептяри	Служилые	мусульмане	нет	39	48	87		
5	Аккузово	Аккузово	Актанышский	тептяри	Служилые	мусульмане	нет	15	17	32		
5	Актаныш	Актаныш	Актанышский	тептяри	Служилые	мусульмане	нет	99	80	179		
5	Алансу Иштеряково тож	Иштеряково	Тукаевский	ясачные татары	Податные	мусульмане	волость	51	38	89		
5	Алметь Муллино	Альметьево	Сармановский	тептяри	Служилые	мусульмане	нет	67	63	130		
5	Алметь Муллино	Альметьево	Сармановский	ясачные татары	Податные	мусульмане	волость	5	2	7		
5	Амекеево	Амикеево	Муслюмовский	тептяри	Служилые	мусульмане	нет	87	94	181		
5	Аняково	Аняково	Актанышский	тептяри	Служилые	мусульмане	нет	70	63	133		
5	Апасево по речке Муртыш	Муртыш-Баш	Сармановский	тептяри	Служилые	мусульмане	нет	56	54	110		
5	Апасево по речке Муртыш	Муртыш-Баш	Сармановский	ясачные татары	Податные	мусульмане	волость	31	34	65		
5	Апасово	Апачево	Актанышский	тептяри	Служилые	мусульмане	нет	1	1	2		
5	Асекеева Пустошь	Азьмушкино	Тукаевский	ясачные татары	Податные	мусульмане	волость	80	95	175		
5	Ахметево	Старое Ахметово	Сармановский	тептяри	Служилые	мусульмане	нет	53	63	116		
5	Ахметево	Старое Ахметово	Сармановский	ясачные татары	Податные	мусульмане	волость	8	5	13		
5	Ахуново	Ахуново	Актанышский	тептяри	Служилые	мусульмане	нет	18	32	50		
5	Ашпала Исангулово тож	Исангулово	Мензелинский	ясачные татары	Податные	мусульмане	волость	52	49	101		

Рис.19. Табличное представление ревизских записей.

При нажатии на каждую запись возникает окно с более подробными сведениями об этой записи (Рис.20).

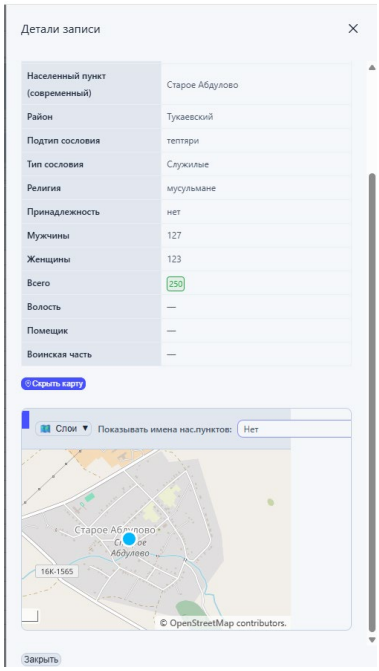

Рис.20. Пример детализации ревизской записи с указанием географического положения.